# Tempo 30 an Schulwegen!

*im Sinne der Allgemeine Verwaltungsvorschrift zur Straßenverkehrs-Ordnung (VwV-StVO)*

© ADFC / Gerhard Westrich

# Allgemeine Verwaltungsvorschrift zur Straßenverkehrs-Ordnung Novelle 24/25

- “entlang **hochfrequentierter Schulwege** [ist] in der Regel auf **Tempo 30 km/h** zu beschränken”
- “Hochfrequentierte **Schulwege** sind **Straßenabschnitte**, die [...] eine **Bündelungswirkung** [...] zwischen Wohngebieten und allgemeinbildenden Schulen haben.”
- “Hochfrequentierte Schulwege können aus **Schulwegplänen** ergeben”
  - durch betroffenen Schulen, zuständigen Straßenverkehrsbehörde, Polizei, Straßenbaubehörde
- **Schulwegpläne** sind im **Schulwegsicherungskonzept** vorgesehen, Verweis auf Leitfaden vom BAST

# Zieldefinition

**Verwaltungsvorschrift StVO 24/25**

**Schulwegpläne**
Schulwegsicherungskonzepts 2018

**36 Schulen** in Potsdam im 100 m Korridor an Tempo 50 Straßen

**Tempo 30 an hochfreq. Schulwegen**
Verwaltungsvorschrift StVO 24/25 umsetzen
Schulwegsicherungskonzepts 2018 umsetzen

**635 Unfälle** in 2024 in unmittelbarer Nähe zu Tempo 50 Straßen (10 m Korridor), **407** davon **mit Fuß/Rad Beteiligung**

**Verkehrssicherheit für Schüler:innen, Unfälle reduzieren**
Impacts messen, Vision Zero

**729 Unfälle** in 2024 mit Fußgänger/Fahrrad im 500 m Umkreis zu Schulen **~ 2/Tag**

# BAST: Fragebögen? not so state-of-the-art!

(**Quelle:** © OpenStreetMap und Mitwirkende, CC-BY-SA, www.openstreetmap.org)

1. Bitte hier den Schulweg Ihres Kindes einzeichnen.
2. Probleme/Gefahrenstellen mit Nummern kennzeichnen.

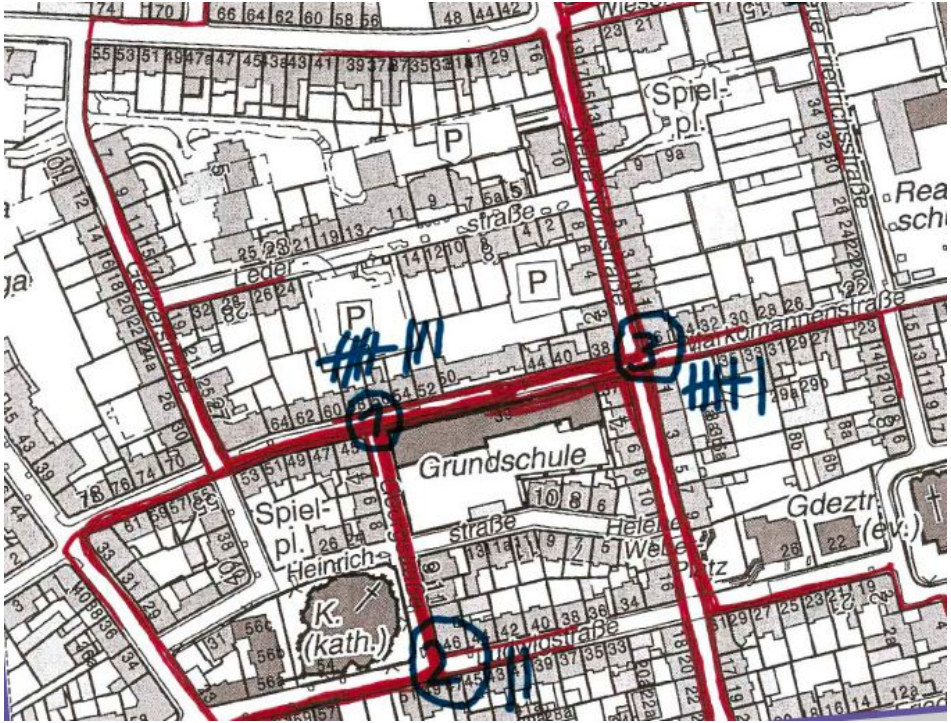

# Datengrundlage: Adressen aller Schülerinnen

- **Adressen** der Schüler:innen grenzen den Schulweg ein
- Annahme: bestrittener Schulweg weicht nicht stark von kürzestem Weg ab
- unterschiedliche Modalitäten müssen nicht modelliert werden
  - können durch Heuristiken angenähert werden

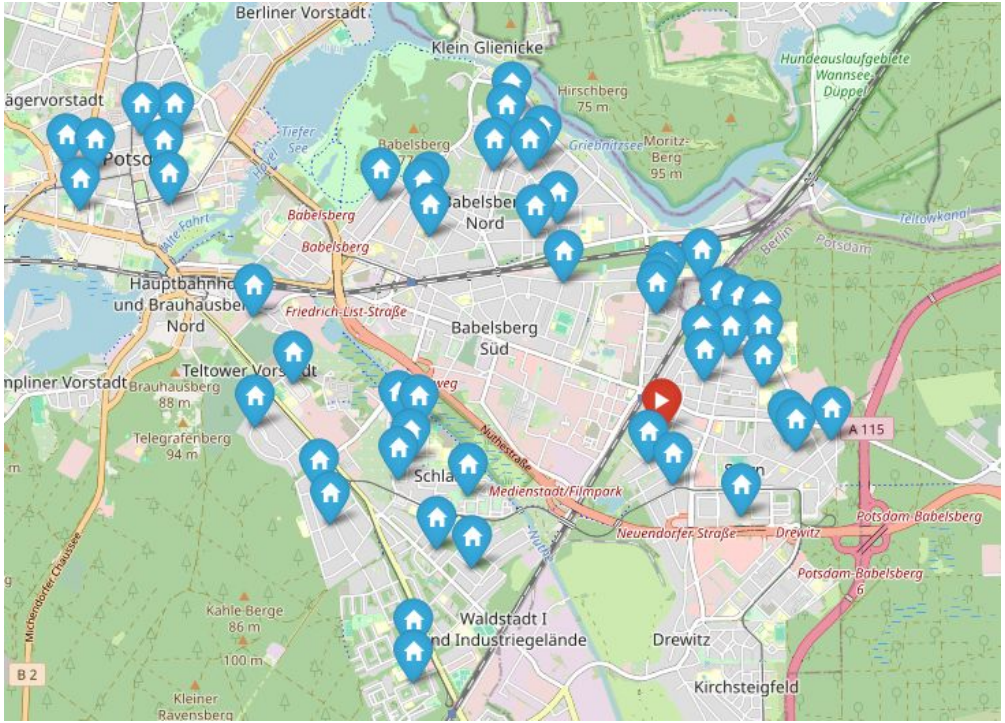


Synthetisch generierte Adressen im Wohnumfeld des Schulzentrums am Stern

Upload GeoJSON/JSON

Drag and drop file here

Limit 200MB per file • GEOJS…

Browse files

Schwellenwert für Segment-Überlappung (zeige Segmente, die von mindestens so vielen Routen verwendet werden)

1

Download Schulwege GeoJSON

# Hochfrequentierte Schulwege

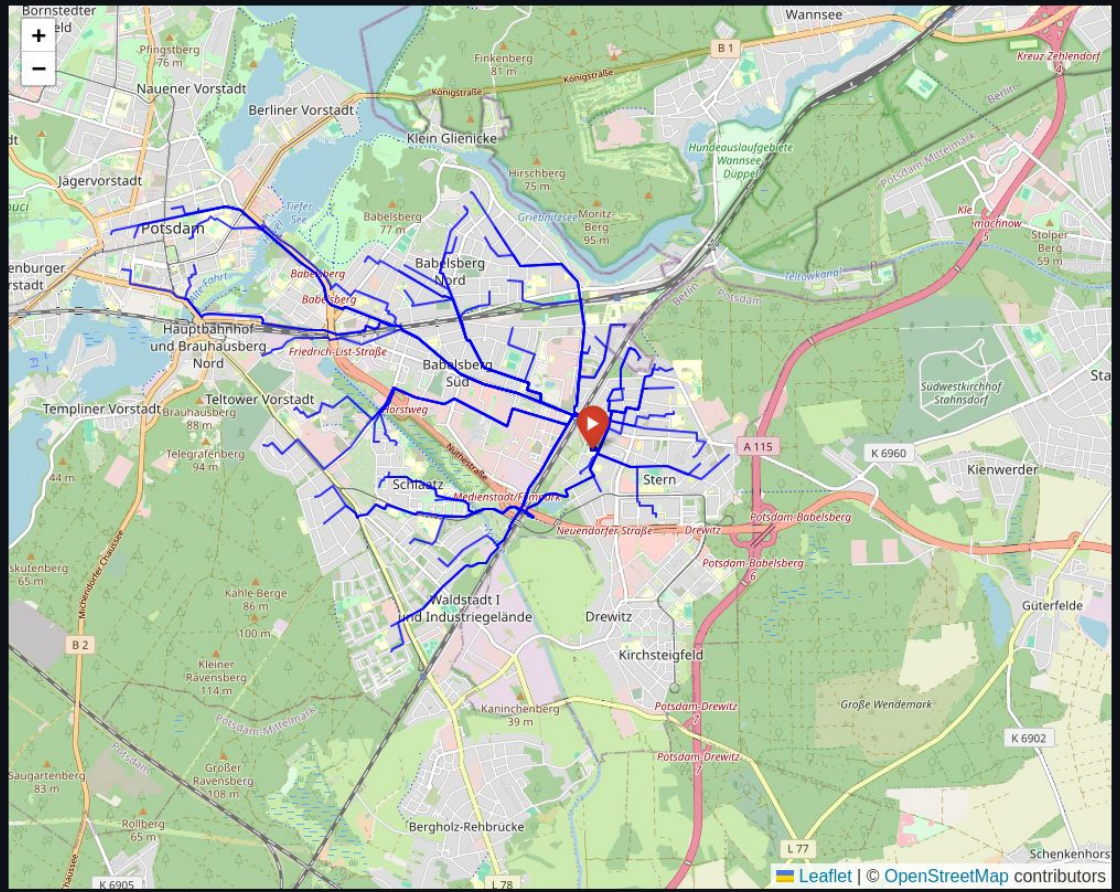

Schwellwert wählen

Upload GeoJSON/JSON

Drag and drop file here

Limit 200MB per file • GEOJS…

Browse files

Schwellenwert für Segment-Überlappung (zeige Segmente, die von mindestens so vielen Routen verwendet werden)

6

Download Schulwege GeoJSON

# Hochfrequentierte Schulwege

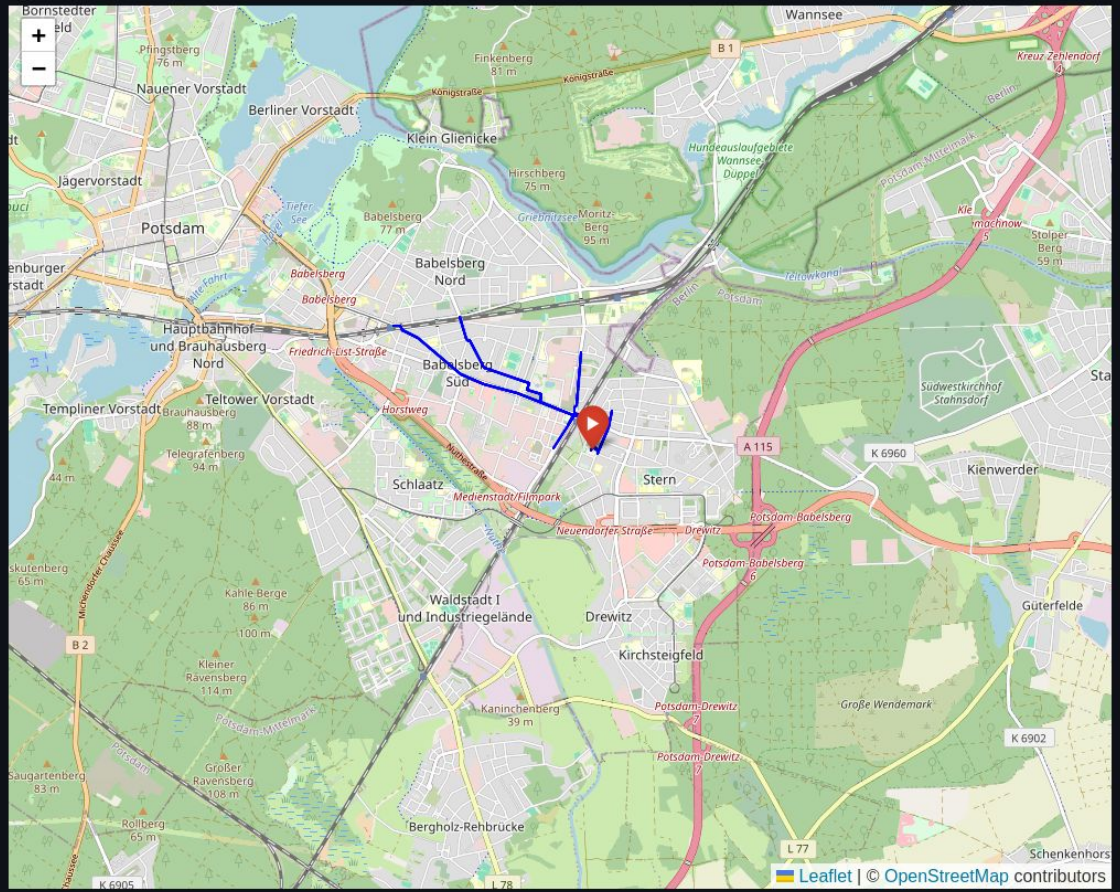

Schwellwert wählen

Upload GeoJSON/JSON

Drag and drop file here

Limit 200MB per file • GEOJS…

Browse files

Schwellenwert für Segment-Überlappung (zeige Segmente, die von mindestens so vielen Routen verwendet werden)

6

Download Schulwege GeoJSON

**Anonyme Hochfrequentierte Schulwege**

# Hochfrequentierte Schulwege

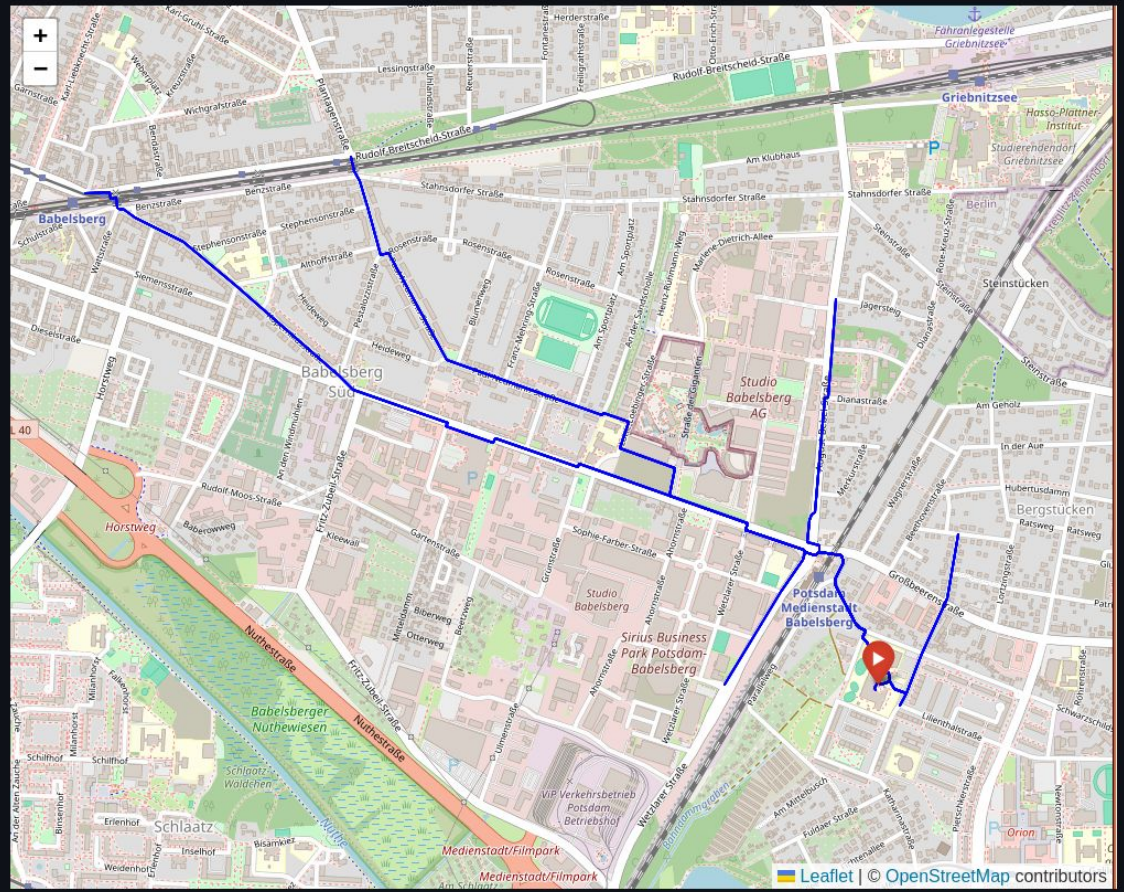

Hochfrequente Schulwege

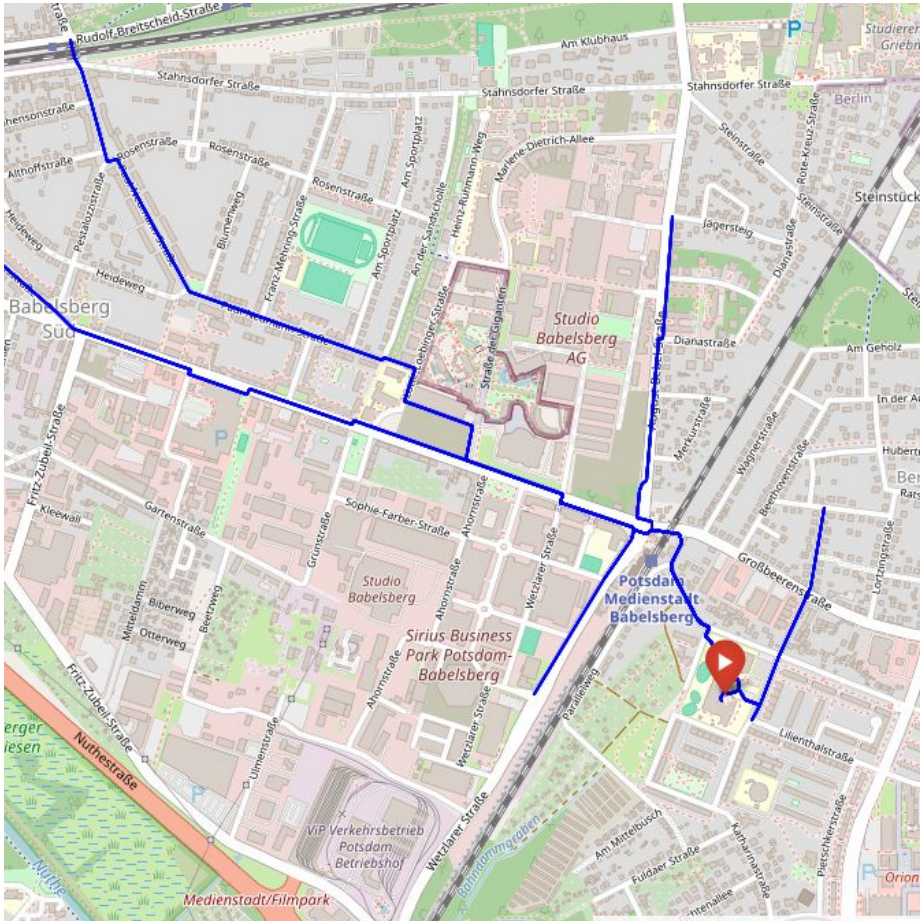


Schulen Tempo 30 Tempo 50

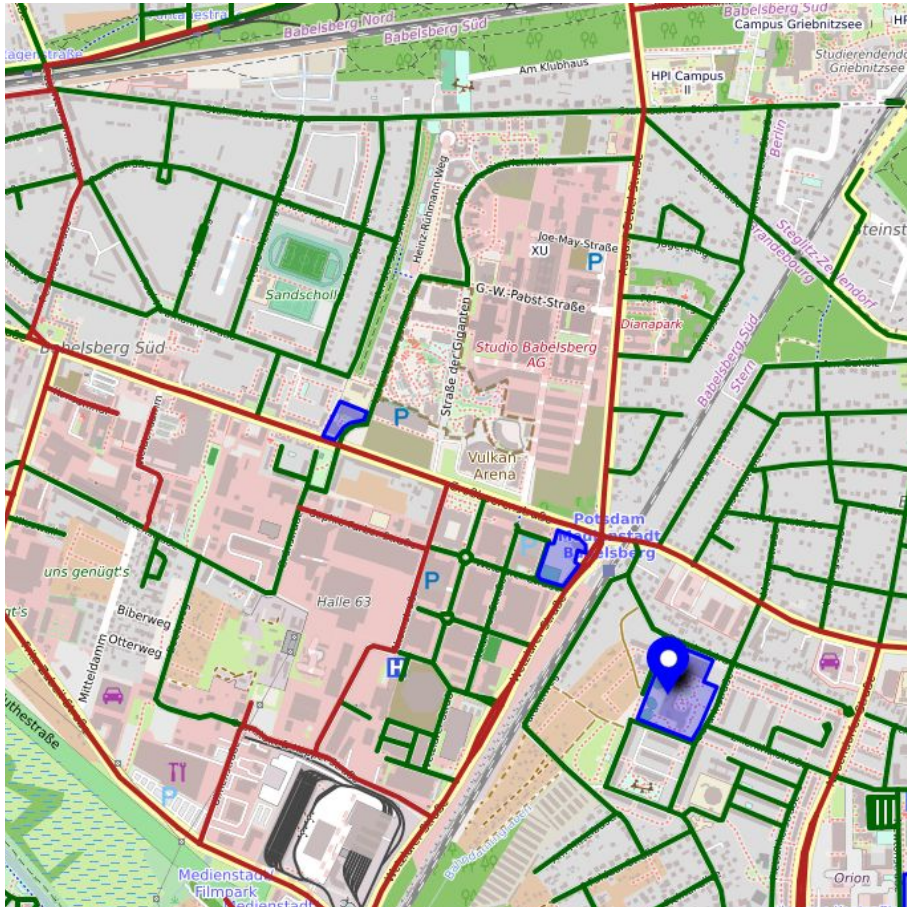

# Nächste Schritte

Unterstützung und Zusammenarbeit für eine
**Vorstellung im**
**Geschäftsbereich Bildung, Kultur, Jugend und Sport**

Unterstützung und Zusammenarbeit für eine
**Vorstellung im Kreiselternrat**

Unterstützung und Zusammenarbeit für **Pilotprojekt**
**Datengetriebener Schulwegplan mit**
**Schulzentrum am Stern**

I**nnerhalb geschlossener Ortschaften** ist die Geschwindigkeit auch entlang **hochfrequentierter Schulwege** in der Regel auf **Tempo 30 km/h** zu beschränken.

Dies gilt insbesondere auch auf klassifizierten Straßen (Bundes-, Landes- und Kreisstraßen) sowie auf weiteren Vorfahrtstraßen (Zeichen 306).

Im **Ausnahmefall** kann auf die Absenkung der Geschwindigkeit verzichtet werden, soweit etwaige negative Auswirkungen auf den ÖPNV (z. B. Taktfahrplan) oder eine drohende Verkehrsverlagerung auf die Wohnnebenstraßen zu befürchten sind.

In die Gesamtabwägung sind Sicherheitsgewinne durch **Sicherheitseinrichtungen** und Querungshilfen (z. B. Lichtzeichenanlagen, Sperrgitter) einzubeziehen.

Die beiden Fahrtrichtungen müssen dabei nicht gleich behandelt werden. Die Anordnungen sind, soweit **Öffnungszeiten** (einschließlich Nach- und Nebennutzungen) festgelegt wurden, auf diese zu beschränken.

**Hochfrequentierte Schulwege sind Straßenabschnitte, die innerhalb eines Stadt- oder Dorfteils eine Bündelungswirkung hinsichtlich der Wege zwischen Wohngebieten und allgemeinbildenden Schulen haben.**

Diese Wege können auch im **Zusammenhang mit der Nutzung des ÖPNV bestehen**.

Ihre Lage ist begründet darzulegen. Sie kann sich auch aus Schulwegplänen ergeben, die von den betroffenen Schulen und der zuständigen Straßenverkehrsbehörde sowie gegebenenfalls Polizei und Straßenbaubehörde erarbeitet wurden.

# Effectiveness of 30 km/h speed limit – A literature review

George Yannis, Eva Michelaraki *

*National Technical University of Athens, Department of Transportation Planning and Engineering, 5 Heroon Polytechniou str., Athens GR-15773, Greece*

ARTICLE INFO

*Keywords:*
30 km/h speed limits
Road safety
Speed limit reduction
Effectiveness
Urban areas

ABSTRACT

*Introduction:* Road crashes are a major social problem, resulting in 1.19 million fatalities and over 50 million injuries annually. Speeding is the primary cause of road crashes worldwide, particularly in cities where pedestrians, cyclists, and motorcyclists are especially vulnerable. This paper aims to review and assess the effectiveness of implementing a 30 km/h speed limit. *Method:* To achieve this objective, a comprehensive literature review was conducted, evaluating the impact of 30 km/h speed limits on safety, emissions, energy consumption, traffic flow, livability, and health. The systematic literature review adhered to the Preferred Reporting Items for Systematic Reviews and Meta-Analyses (PRISMA) guidelines. *Results:* Current scientific evidence indicated that the introduction of 30 km/h speed limits in cities can save over 40% of lives, alongside significant positive effects on the environment, energy consumption and public health, including reduced fuel consumption and increased walking and cycling. *Practical Applications:* Public awareness campaigns and promoting the use of public transport and active mobility options, such as walking and cycling, could further support the adoption of 30 km/h speed limits in cities.

**Table 3**
Maximum and average values of the quantitative effect of 30 km/h speed limits.

| | Max | Average |
|---|---|---|
| **Crashes** | −60% | **−30%** |
| **Crashes (pedestrians)** | −70% | **−43%** |
| **Crashes (cyclists)** | −48% | **–33%** |
| **Fatalities** | −63% | **−45%** |
| **Fatalities (pedestrians)** | −67% | **−46%** |
| **Injuries** | −63% | **−40%** |
| **Injuries (pedestrians)** | −67% | **−61%** |
| **Injuries (cyclists)** | −55% | **−38%** |
| **$CO_2$ emissions** | −25% | **−20%** |
| **$NO_x$ emissions** | −48% | **−35%** |
| **PM emissions** | −45% | **−20%** |
| **Noise** | −5 dB | **−3.7 dB** |
| **Fuel consumption** | −11% | **−7%** |
| **Traffic volumes** | −30% | **−16%** |
| **Travel times** | +5% | ***no impact*** |

# Adolescents' travel behavior in Germany: Investigating transport mode choice considering destination, travel distance, and urbanization

Isabel Marzi [a,*], Franziska Beck [a], Eliane Engels [a], Denise Renninger [b], Yolanda Demetriou [b], Anne K. Reimers [a]

[a] Department of Sport Science and Sport, Friedrich-Alexander-Universität Erlangen-Nürnberg, Gebbertstr. 123b, 91058 Erlangen, Germany
[b] Department of Sport and Health Sciences, Technical University of Munich, Georg-Brauchle-Ring 62, 80992 Munich, Germany

ARTICLE INFO

*Keywords:*
Active commuting
Independent mobility
Physical activity
Girls
Boys
School

ABSTRACT

This study comprehensively describes travel behavior to various destinations among adolescents from Germ
aged 11–15 years and how this varies according to residential location type and adolescents' socio-demograph
Overall, more than a half of adolescents use active transport modes to reach school and non-school destinati
Prevalence of passive transport modes was higher in girls compared to boys, on the way to and from sch
compared to non-school destinations, and for longer distances. Adult accompaniment occurred predominantl
non-school destinations, was higher in girls compared to boys and was associated with passive travel. In
future, active travel promotion programs should especially consider girls' needs to prevent low levels of ac
travel. Additionally, improvements in the public transport infrastructure are recommended to enable a shift
healthy and sustainable travel behavior in adolescents.

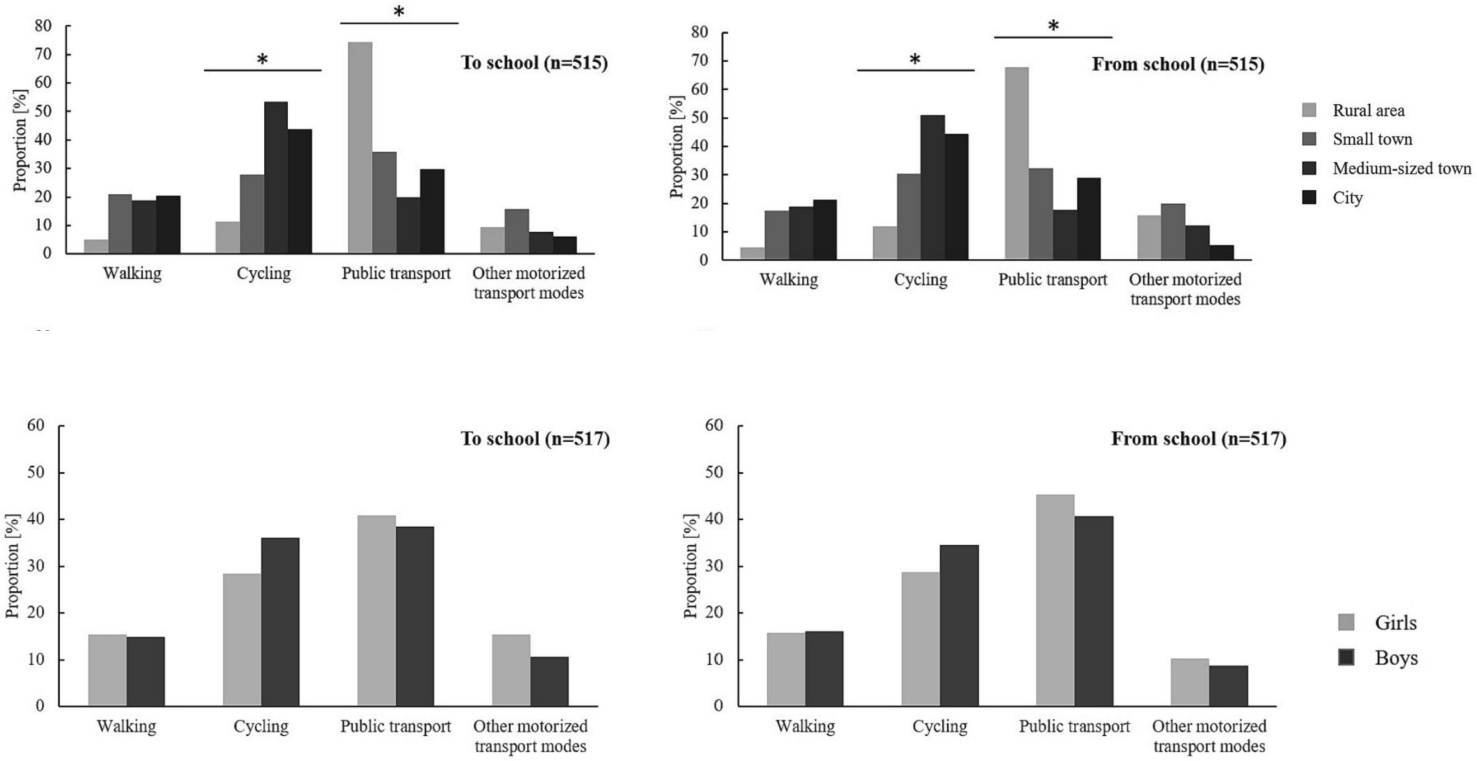
To school (n=515)
From school (n=515)
To school (n=517)
From school (n=517)
Proportion [%]
Walking
Cycling
Public transport
Other motorized transport modes
Rural area
Small town
Medium-sized town
City
Girls
Boys
*

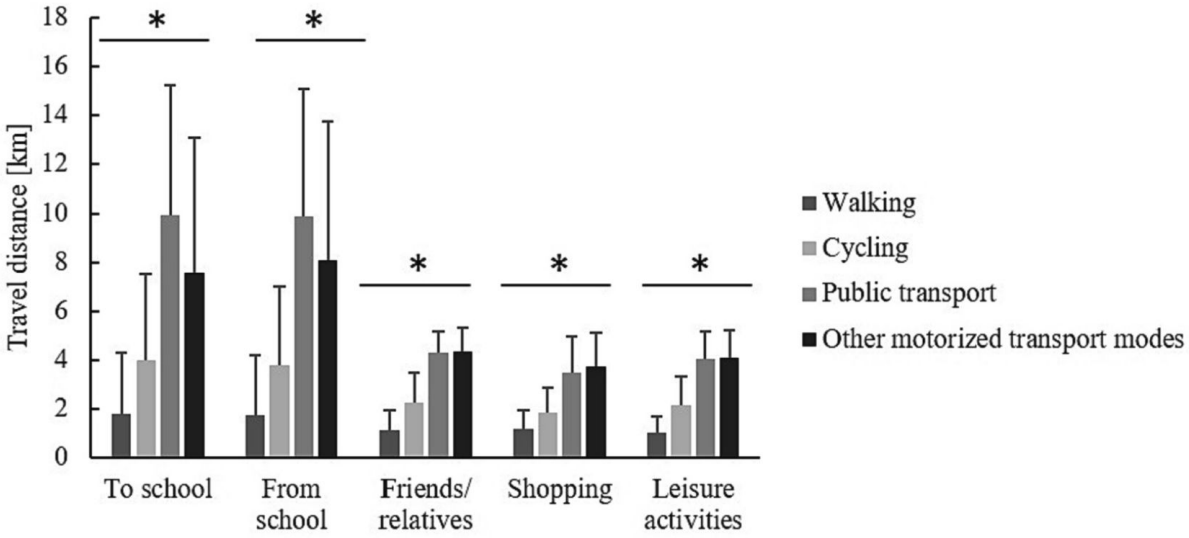
Travel distance [km]
18
16
14
12
10
8
6
4
2
0
*
*
*
*
*
To school
From school
Friends/ relatives
Shopping
Leisure activities
Walking
Cycling
Public transport
Other motorized transport modes

# Unfälle an Schulen (Unfallatlas 2024, OSM)

| Umkreise Schulen (m) | Anzahl Unfälle | davon Fuß/Rad Beteiligung |
|---|---|---|
| **500** | 986 | 729 |
| **1.000** | 3.361 | 2.292 |
| **2.000** | 10.098 | 6.838 |

- 2024 ereigneten sich in Potsdam **635 Unfälle** in unmittelbarer Nähe zu T50 Straße (10 m Korridor), **407 davon mit Fuß/Rad Beteiligung**
- **36 Schulen** in Potsdam sind im 100 m Umkreis einer T50 Straße